Google Traducido al: español Mostrar texto original Opciones ▼

SHENZHEN YUSHENGCHANG TECNOLOGÍA CO.,LTD

Guía de configuración del portal del servidor

Vistas: 4397 Autor: Editor del Sitio Hora de publicación: 2019-10-30 Origen: Sitio

Guía de configuración del servidor

1. Se puede acceder al dominio , pero es fácil desconectarse porque no es estable. No estoy seguro de si el DNS se analiza al 100 %. Sugerimos usar el servidor de socket TCP/IP.

i) Se puede usar la dirección de dominio del servidor o la dirección IP, siempre que garanticen el análisis correcto del nombre de dominio. El uso de la IP se realiza para evitar errores en el análisis del nombre de dominio.

ii) Nuestro protocolo es TCP/IP , no HTTP, no https

iii) Toda comunicación GPRS , no UDP, no es adecuada para la configuración del cable de datos

iii) Toda comunicación GPRS , no UDP , no es adecuada para la configuración del cable de datos.

Idioma del software de la aplicación: la versión de Android es Java ; la versión de IOS es Object C

El lenguaje del software que ejecuta el servidor es Node.JS

El software del firmware es lenguaje C

Es un servidor de socket TCP/IP , solo comunicación GPRS, el cifrado de clave es AES128 , sin MQTT

Lo más importante es que el dispositivo envíe cualquier Linkkeep, su servidor necesita responder o confirmar el Linkkeep para el mantenimiento de la conexión de red.

Al comienzo de la media hora, el dispositivo envía el Linkkeep cada minuto; si está conectado/en línea, después de media hora, envía el Linkkeep cada 5-8 minutos.

Este es un protocolo de enlace, por lo que se conocen entre sí para mantener la conexión de red, si no, la red se desconecta.

TKQ2 es un mensaje de voz fuera de línea

2. ¿Utilizas una API de Google para la posición? Si no es así, quizás deberías buscarla: https://developers.google.com/maps/documentation/geolocation/intro

Es importante tener en cuenta que todos los dispositivos GPS que funcionan en interiores tendrán un gran error de GPS, y que la información de LBS y WiFi necesita una buena fuente de datos y también una base de datos altamente actualizada de esos ID en la API de geolocalización de Google.

Necesitará agregar procesamiento adicional al algoritmo de ubicación para evitar saltos de satélite, datos corruptos, ubicaciones con baja precisión, mejorar el uso de wifi, etc. Esta es una buena práctica en cualquier software LBS. Aquí depende de usted la lógica que desee usar: calcular promedios, comparar con datos históricos del mismo dispositivo, bloquear la posición siempre cuando el GPS no esté fijo, etc.

3. La IP y el puerto del servidor solo se pueden cambiar desde el servidor. El IMEI debe estar registrado en el servidor, que identifica el dispositivo mediante su número de identificación. Tras cambiar la IP y el puerto desde

el servidor, simplemente reinicie el dispositivo y espere de 6 a 8 minutos. Para comprobar la respuesta del ts#, verá si la conexión del servidor se ha realizado correctamente.

when we take our "IMEI" and ID number and match them to the specification format, we' ll get

	1 7 0 3	2 1 5 9 1 1	— ID number
8 6 8 0	1 7 0 3	2 1 5 9 1 1 8	— IMEI number
TAC		**SN**	**CD**
allocated number		serial number	control digit

Matched ID to the IMEI:IMEI is 15 numbers ,remove the front 4 numbers and remove the last number then is 10 numbers , this is the device ID number .IMEI number registered in server , the server identify the device per ID number .

GPS con micrófono y altavoz, es un sistema de teléfono con funciones, con tarjeta SIM para funciones de voz + datos.

El sistema GPS consta de un conjunto de chips IC de teléfono con funciones + modo GPS + modo WiFi (opcional)

El GPS funciona con la aplicación del teléfono: de teléfono a teléfono, de máquina a máquina.

4. Este es el ejemplo para mostrarle los datos del extremo del servidor.

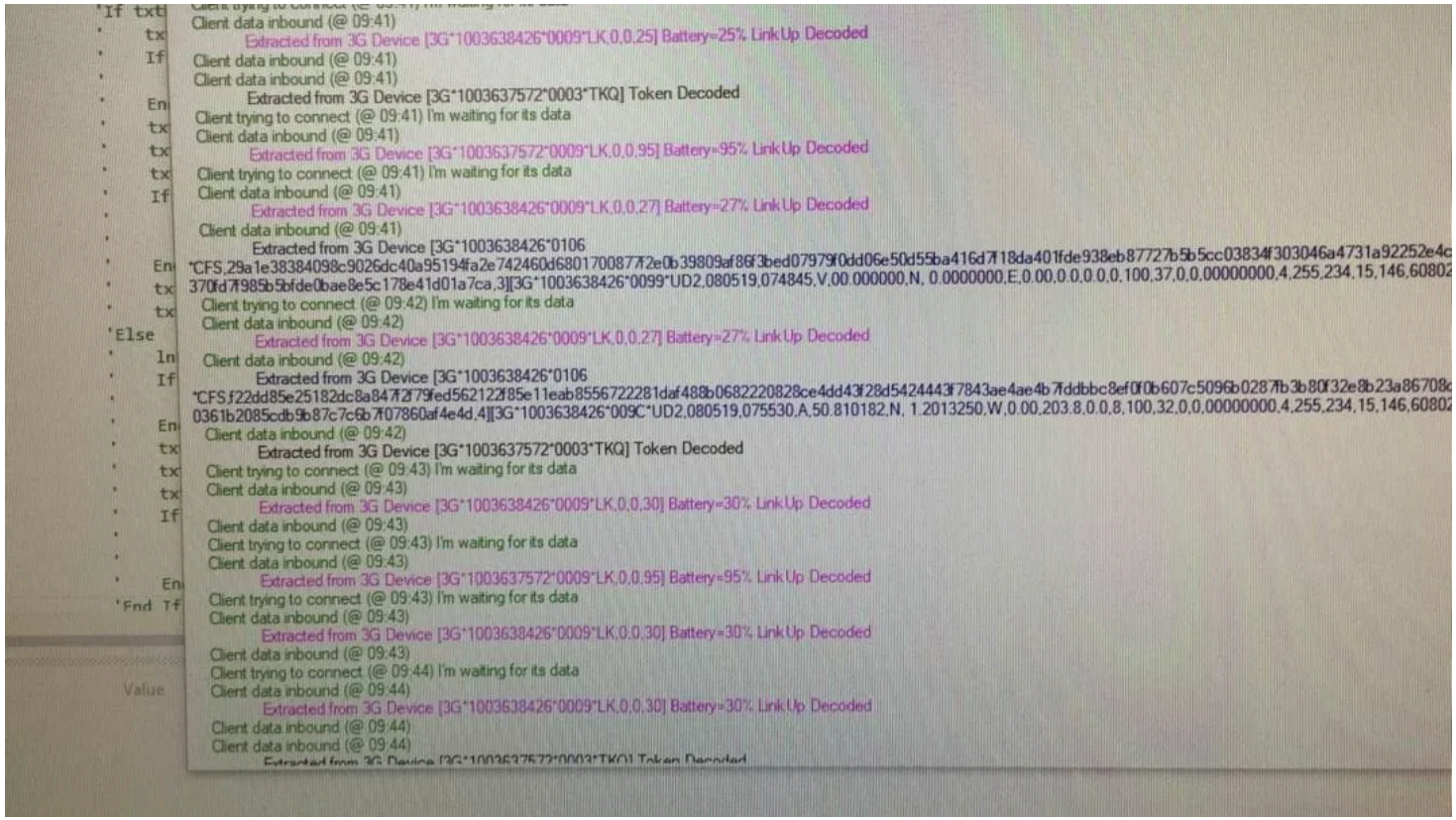

Todos los HEX . necesitan convertirse a código ASCII

i) Enlace de mantenimiento:

HEXAGONAL : 5B33472A303330343138373130392A303030392A4C4B2C302C302C32315D

ASCII : [3G*0304187109* 0009 * LK,0,0,21]

y debería recibir una respuesta igual a la montada: [3G*0304187109* 0002 * LK]

Ejemplo:[CS*AAAAAAAAAA* LEN * LK]

[3G*8800000015* 0002 * LK]---la longitud se modifica según la longitud del contenido

Dispositivo de envío:

[CS*YYYYYYYYYY* LEN *LK, paso, número de volteretas, porcentaje del estado de la batería]

Ejemplo: [3G*8800000015* 000D * LK,50,100,100]

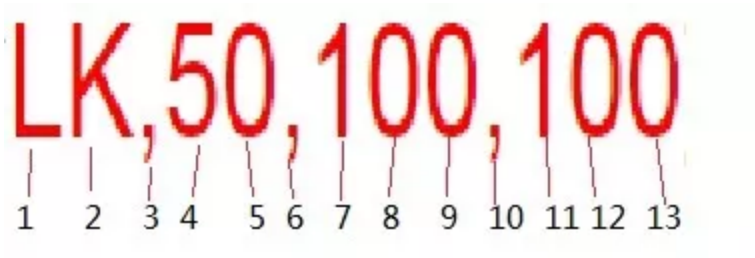

ii) mensaje:

HEXAGONAL : 5B33472A303330343138373130392A303030392A46465A4450415948355D

ASCII : [3G*0304187109*0009*FFZDPAYH5]

iii) Alerta SOS con código diferente (AL_LTE):

HEXAGONAL :
5B33472A303330343138373130392A303132302A414C5F4C54452C3331303132302C3138343235312C562C302E302C4E2C302E302C452C32322E302C302C2D

312C302C3130302C31312C302C302C303030313030030312C312C312C3333342C3

032302C31333031312C32333135323135342C3130302C352C52454355504552414

3494F4E534C542C37383A38613A32303A38313A65363A64662C2D35342C524543
555045524143494F4E534C542C37383A38613A32303A38313A66623A65382C2D3

6342C52454355504552414349 4F4E534C542C37383A38613A32303A38313A6536
3A65302C2D36352C41524C4F5F564D425F313536323739383634372C38633A3362

3A61643A66623A35393A38362C2D37332C4C757A3030322C30633A66383A39333A37623A66383A31302C2D383
52C302E305D

ASCII : [3G*0304187109*0120* AL_LTE
,310120,184251,V,0.0,N,0.0,E,22.0,0,-1,0,100,11,0,0,00010001,1,1,334,020,13011,23152154,100,5,RECOVERYSLT,
78:8a:20:81:e6:df,

-54,RECUPERACIONSLT,78:8a:20:81:fb:e8,-64,RECUPERACIONSLT,78:8a:20:81:e6:e0,-
65,ARLO_VMB_1562798647,8c:3b:ad:fb:59:86,-73,Luz002,0c:f8:93:7b:f8:10,-85,0.0]

iv) Mensaje de posición con código diferente (UD_LTE):

HEXAGONAL :
5B33472A303330343138373130392A303132302A55445F4C54452C3331303132302C3138343334372C562C302E
302C4E2C302E302C452C32322E302C302C2D312C302

C3130302C31312C302C302C302C30303030303030312C312C312C3333342C3032302C
31333031312C32333135323135312C3130302C352C52454355504552414349 4F4E534C

542C37383A38613A32303A38313A65363A64662C2D35342C524543555045524143
494F4E534C542C37383A38613A32303A38313A66623A65382C2D36342C524543555

045524143494F4E534C542C37383A38613A32303A38313A65363A65302C2D36352
C41524C4F5F564D425F313536323739383634372C38633A33623A61643A66623A35

393A38362C2D37332C4C757A3030322C30633A66383A39333A37623A66383A31302C2D38352C302E305D

ASCII : [3G*0304187109*0120*UD_LTE,310120,184347,V,0.0,N,0.0,E,22.0,0,-1,0,100,11,0,0,

ASCII : [3G*0304187109*0120*UD_LTE,310120,184347,V,0.0,N,0.0,E,22.0,0,-1,0,100,11,0,0

,00000001,1,1,334,020,13011,23152151,100,5,RECOVERYSLT,78:8a:20:81:e6:df,

-54,RECUPERACIONSLT,78:8a:20:81:fb:e8,-64,RECUPERACIONSLT,78:8a:20:81:e6:e0,-65,ARLO_VMB_1562798647,8c:3b:ad:fb:59:86,-73,Luz002,0c:f8:93:7b:f8:10,-85,0.0]

Device status	00000000(Hexadecimal)	Indicated with HEX string of character , the meaning is as follows: The high 16bit expression alarming, low 16bit expression condition(from left to right). The Bit position (0 starts) Meaning (1 Effective) 0 Low battery state 1 out of fence state 2 Enter the fence state 3 watch state 4 Device no moving state 16 SOS alarm 17 Low battery alarm 18 out fence alarm 19 Into the fence alarm 20 Remove the watch alarm 21 Fall down alarm 22 Abnormal heart rate alarm

v) El bit de alarma de nuestro protocolo es hexadecimal de 8 bits, y un hexadecimal se compone de binario de 4 bits.

4*8 es de 32 bits, y nuestro protocolo puede representar un estado de 32 bits, de los cuales los 16 bits inferiores representan el estado (nuestro GPS no tiene ningún estado) y los 16 bits superiores representan la alarma **(cuenta de derecha a izquierda, el 1.er bit es 0, comienza con 0)** , pero la alarma solo una vez, la alarma de batería baja, el 17.º bit es 00020000, la alarma SOS, el 16.º bit es 00010000, si ambas alarmas juntas, deben ser 00030000; el 21.º bit de la alarma de caída es 00200000

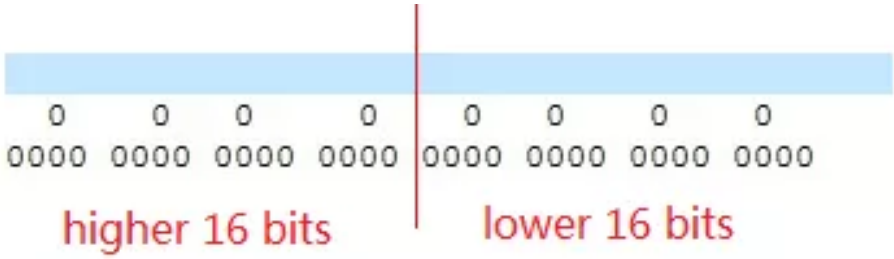

La parte superior es

hexadecimal, la inferior es binaria.

0000	0000	0000	0010	0000	0000	0000	0000

Tenga en cuenta que el dispositivo GPS obtiene la posición física en un tiempo de 3 minutos y envía el UD cada 20 segundos.

Normalmente recibir 6, 9 o 12 UD está bien, pero V es una posición GPS no válida en UD, solo A es una posición GPS válida en UD

Después del comando CR del servidor, aparece 6UD, 9UD o 12 UD, lo cual es normal; solo se toma la posición GPS válida en la cadena UD.

5. A continuación se muestra únicamenteel **protocolo del podómetro.**

Configuración del tiempo de caminata* (podómetro)

Plataforma de envío:

[CS*YYYYYYYYYY*LEN*WALKTIME, sección de tiempo, sección de tiempo, sección de tiempo]

Ejemplo: [3G*5678901234*002A* TIEMPO DE CAMINATA , 8:10-9:30, 10:10-11:30, 12:10-13:30]

Respuesta del dispositivo:

[CS*AAAAAAAAAA*LARGO*CUALQUIERA]

Ejemplo: [3G*5678901234*0008*TIEMPO DE CAMINATA]

Nota: configure la sección de tiempo de conteo de pasos del tiempo de caminata.

Nota: El dispositivo registra dos valores, uno es el número de pasos por día, que se restablecerá cada día, y el otro es el número total acumulado de pasos, que no se restablecerá. Lo que el dispositivo informa a el servidor es el número total de pasos, y el servidor debe calcular el número de pasos por día en función sobre el número total de pasos subidos

6. Informe de datos de HR y BPM al mismo tiempo, esta es la configuración que se necesita ahora para todos nuestros GPS senior, por favor informe a su equipo.

i) Este es el extremo del servidor remoto para obtener el protocolo de fecha de FC y PA.

*Solicitud remota de plataforma Frecuencia cardíaca y presión arterial:

Plataforma de envío:

[3G*8800000015*len*hrtstart,x]

x es 1 significa que el dispositivo carga los datos de frecuencia cardíaca una sola vez y luego se detiene automáticamente después de la carga.

Por ejemplo:[3G*9513979338*000a*hrtstart,1]

x es 0 significa que el dispositivo dejó de cargar los datos de frecuencia cardíaca.

Respuesta del dispositivo:

[3G*8800000015*len*hrtstart]

[3G*8800000015*0013 * bphrt,112,73,67,,,,]

Presión arterial sistólica: 112

Presión arterial diastólica: 73

Frecuencia cardíaca: 67

ii) Este es el protocolo que informa los datos de FC y PA del dispositivo al servidor.

Carga de frecuencia cardíaca y presión arterial (ambas miden al mismo tiempo)

Carga del dispositivo:

[3G*8800000015*len*bphrt , xx,xx,xx,xx,xx,xx,xx]

El primer parámetro xx representa alta presión y 0 significa inválido.

El segundo parámetro xx representa baja presión y 0 significa inválido.

El tercer parámetro xx representa una frecuencia cardíaca de 0 para valores no válidos

El tercer parámetro xx representa una frecuencia cardíaca de 0 para valores no válidos.

El cuarto parámetro xx representa la altura en cm.

El quinto parámetro xx representa el género 1 es masculino 2 es femenino

El sexto parámetro xx representa la edad.

El séptimo parámetro xx representa el peso en KG

Respuesta de la plataforma:

[3G*8800000015*0005*bphrt]

(Tenga en cuenta que SPO2 son datos de algoritmo en la aplicación y en el servidor; después de configurar FC y PA en su servidor, los datos de SPO2 serán automáticos en el servidor).

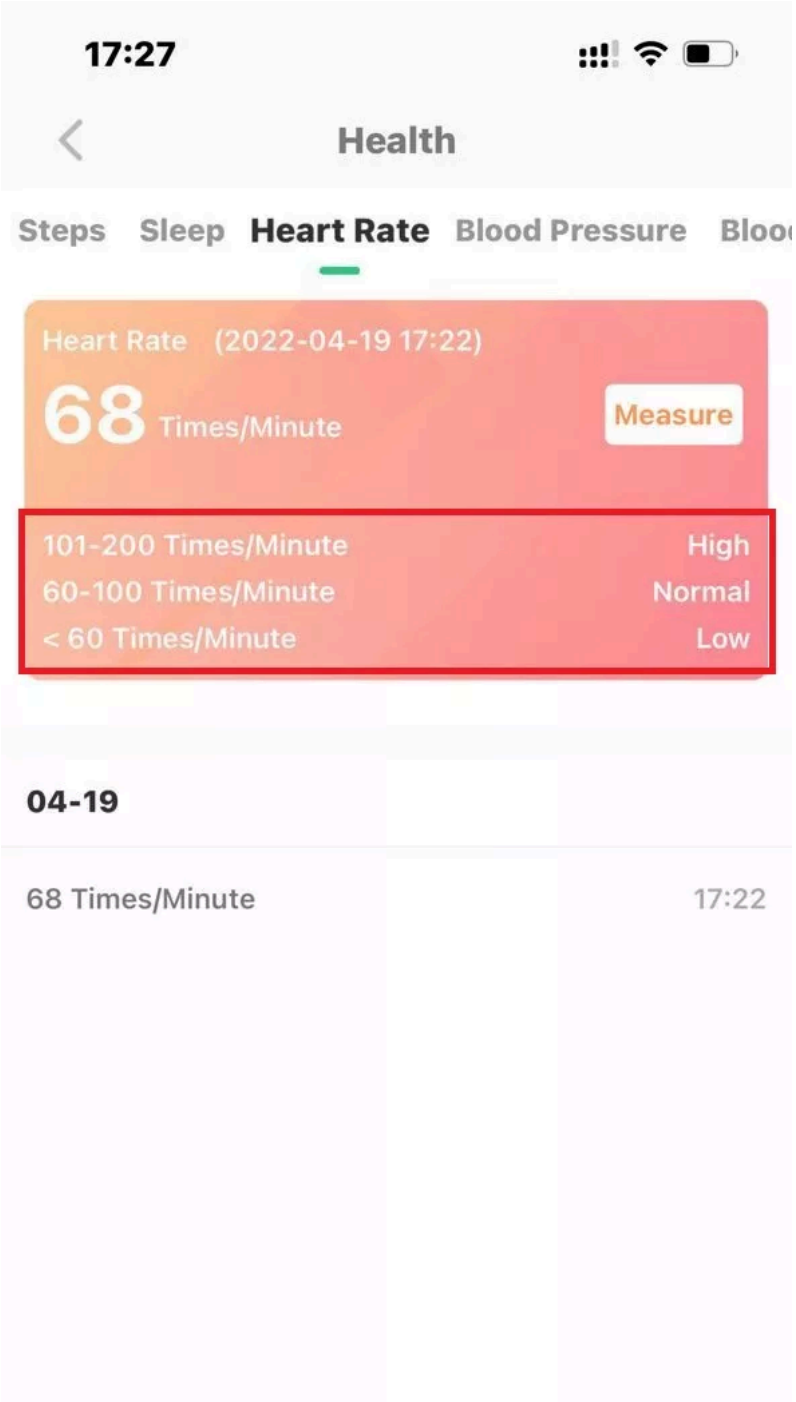
17:27
Health
Steps
Sleep
Heart Rate
Blood Pressure
Bloo
Heart Rate (2022-04-19 17:22)
68 Times/Minute
Measure
101-200 Times/Minute High
60-100 Times/Minute Normal
< 60 Times/Minute Low
04-19
68 Times/Minute 17:22

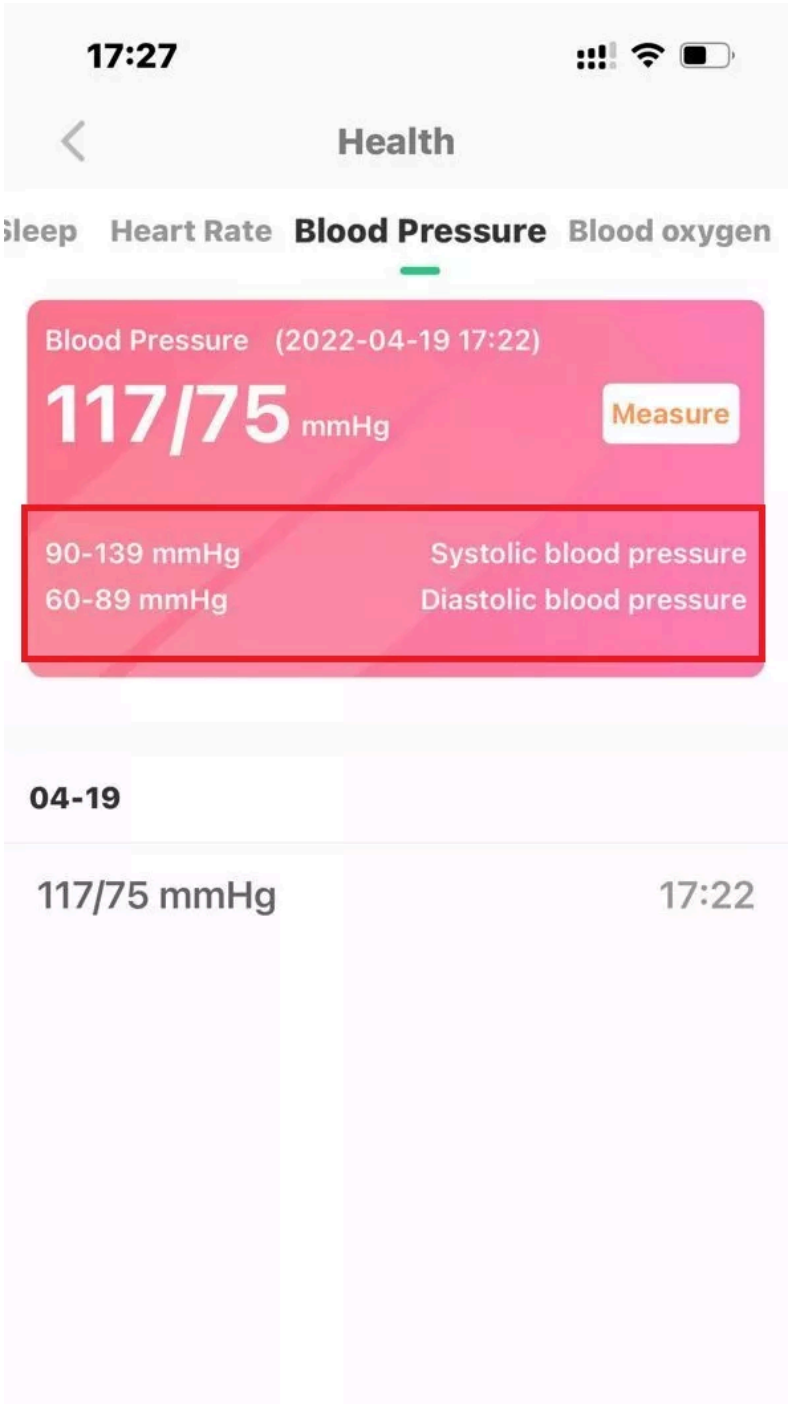
17:27
Health
Sleep
Heart Rate
Blood Pressure
Blood oxygen
Blood Pressure (2022-04-19 17:22)
117/75 mmHg
Measure
90-139 mmHg
Systolic blood pressure
60-89 mmHg
Diastolic blood pressure
04-19
117/75 mmHg
17:22

17:27
Health
Sleep
Heart Rate
Blood Pressure
Blood oxygen
Blood oxygen (2022-04-19 17:22)
97 %
90% - 100% Good
70% - 89% Average
< 70% Poor
04-19
97%
17:22

7. La cerca geográfica se establece en el extremo del servidor, no en el extremo de la aplicación.

8. Tenga en cuenta que si el dispositivo no se sacude ni se mueve de una orientación diferente durante 2 minutos, pasará automáticamente al modo de hibernación, pero si se sacude o se mueve de una orientación diferente, se reactivará inmediatamente.

Durante la hibernación, solo Linkkeep, no se transfieren datos.

En caso de desconexión, no hay red, no se mantiene el enlace y no se transfieren datos. Sin embargo, al conectarse a la red, el dispositivo actualizará la posición inmediatamente.

9. Si su servidor finaliza la recepción constante de los datos CONFIG del dispositivo, este es el comando de configuración del dispositivo; su servidor puede responder al comando para detenerlo.

[3G*7703713643*0008*CONFIG,1]

Otro comando, si no es necesario, simplemente respóndelo para detenerlo en el extremo del servidor si el dispositivo continúa enviándolo repetidamente.

p. ej.: [3G*7103000140*0005*ICCID]

[3G*7103000140*0006* RYIMEI]

[3G*7103000140*000D* APPCONTACTTEL]

Tenga en cuenta que el dispositivo GPS 4G usa el IC del teléfono inteligente, por lo que muchos comandos y datos también los desconocemos, es algo relacionado con las características del teléfono, si algún dato no es correcto para verificar en el protocolo, simplemente ignórelo o deténgalo.

Anterior: Un cliente de Brasil nos vis...

Siguiente: ¿Por qué el rastreador GP...

Rastreador GPS personal | Seguimiento GPS | Dispositivo de seguimiento GPS | Rastreador GPS personal 4G | Rastreador GPS portátil | Localizador GPS | Rastreador GPS | Mini rastreador GPS | Rastreador GPS para niños | Dispositivo rastreador GPS

Shenzhen Yushengchang Technology
Co., Ltd

Descargar APP

Beesure GPS

Download on the App Store

GET IT ON Google play

CONTÁCTENOS

Alan Tong

+86 13509607927

ventas@4p-touch.com

Le damos una cálida bienvenida a nuestro sitio web. Atentamente, Alan Tong Shenzhen Yushengchang Technology Co., Ltd. Tel.: 86-755-29755516 Fax: 86-755-29755866 Móvil: +86 (0)13509607927 (WeChat y WhatsApp) Correo electrónico: sales@4p-touch.com Skype: alantong718 Sitio web: http://4p-touch.en.made-in-china.com/ www.4p-touch.com

*Código de verificación

c 3 1 i

Entregar

Copyright © 2025 Shenzhen Yushengchang Technology Co., Ltd. Todos los derechos reservados

Número de registro del PCI de Guangdong: 13064141-1